2026-02-16

8 spotkań 17:30 - 19:45 + 1 z lekarzem

- 16.02
- 17.02
- 18.02
- 20.02
- 23.02
- 24.02 — lekarz
- 25.02
- 26.02
- 27.02

80% obecności na wykładach (7 spotkań)

Egzamin z teorii

- Jest taki sam jak w WORD
- 32 pytania: 20 przepisy + 12 wiedza specjalistyczna — 25 min czasu (zaliczenie $\geq \frac{68}{74}$ pkt)

Egzamin praktyczny

- Trwa około 45 min
- Musimy wiedzieć na czym polega
- Maksymalnie 5 minut na obsługę (sprawdzenie) samochodu
- Polecenia od egzaminatora będą zgodne z przepisami ruchu drogowego

---

Definicja 0.1: Pojazd silnikowy

Napędzany mechanicznie pojazd, który porusza się dzięki własnemu napędowi a nie jest motorowerem ani pojazdem szynowym

Definicja 0.2: Pojazd samochodowy

Pojazd silnikowy, którego konstrukcja umożliwia jazdę z prędkością przekraczającą 25 km/h. Określenie to nie obejmuje ciągnika rolniczego

Kategoria B

Definicja 0.3: DMC

Dopuszczalna masa całkowita (masa własna + maksymalny ładunek)

Definicja 0.4: RMC

Rzeczywista masa całkowita (masa własna + rzeczywisty ładunek)

Uprawnia do kierowania pojazdem samochodowym o DMC do 3.5 t

Opcjonalnie plus:

- Przyczepa o DMC do 750 kg **lub**
- Przyczepa dowolna ale łączna DMC zespołu ≤ 3.5 t

RMC przyczepy nie może być większa od RMC pojazdu

Rodzaje skrzyżowań

- Równorzędne
- Z pierwszeństwem
- O ruchu okrężnym (ronda)

Definicja 0.5: Wymuszenie pierwszeństwa

Zmuszenie innego uczestnika ruchu do istotnej zmiany kierunku lub prędkości poruszania się

Równorzędne

Rysunek 1: A-5: Skrzyżowanie równorzędne

Kolejność przejazdu:

1. Pojazdy uprzywilejowane:

Definicja 0.6: Pojazd uprzywilejowany

Mający **łącznie**:

- Sygnał świetlny niebieski
- Sygnał dźwiękowy
- Światła mijania (krótkie) lub drogowe (długie)

Zaliczamy również kolumnę (na początku i na końcu uprzywilejowane mające dodatkowo sygnał świetlny czerwony)

Wskazówka 1

- Możemy wyprzedzić poza obszarem zabudowanym (nie zbliżając się bliżej niż na 100 metrów)
- Kolumny nie możemy wyprzedzić, zachowujemy 100m dystansu

2. Pojazd szynowy (tramwaj)
3. Pojazd z prawej strony

Definicja 0.7

- Omijanie — objeżdżanie przeszkody
- Mijanie — rozjazd z samochodem poruszającym się z przeciwnym kierunku
- Wyprzedzanie — rozjazd z samochodem poruszającym się z tym samym kierunku

Wskazówka 2: Wyprzedzanie

Wyprzedzając pojazd jednośladowy lub kolumnę pieszych musimy zachować odstęp 1 metr

Z drogą posiadającą pierwszeństwo przejazdu

Działamy zgodnie ze znakami D-1, A-7, B-20

Rysunek 2: Znak D-1: Droga z pierwszeństwem



Rysunek 3: Znak A-7: Ustąp pierwszeństwa

Rysunek 4: Znak B-20: Stop

Z ruchem okrężnym

Rysunek 5: C-12: Ruch okrężny

Standardowo wjeżdżający ma pierwszeństwo, jednak zwykle mamy znak A-7: wjeżdżający ustępuje pierwszeństwo

Włączenie się do ruchu

Definicja 0.8: Włączający się do ruchu

Pojazd który rozpoczyna jazdę po zatrzymaniu które nie było spowodowane przepisami ruchu drogowego

Wskazówka 3

Wyjeżdżając ze strefy zamieszkania, strefy ruchu, drogi wewnętrznej lub z pasu ruchu dla pojazdów powolnych jesteśmy włączającym się do ruchu
Pojazd szynowy wyjeżdżający z zajezdni lub z pętli też jest włączającym się do ruchu

Obszar zabudowany

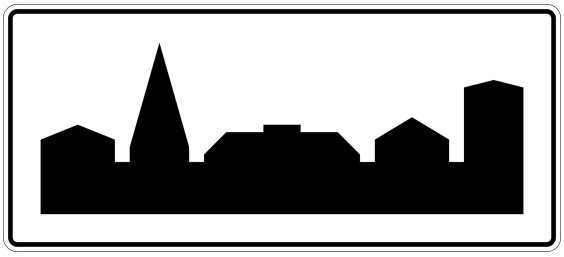

Rysunek 6: D-42: Obszar zabudowany

Podstawowe obowiązki w obszarze zabudowanym:

- Prędkość do 50 km/h
- Zmieniamy światła drogowe na światła mijania
- Przepuszczamy transport publiczny wyjeżdżający z przystanku

---

2026-02-17

Światła

Definicja 0.9: Pozycyjne

Widoczne w nocy przy dobrej przejrzystości powietrza z 300m

Definicja 0.10: Mijania

Oświetlają drogę na min 40m i są asymetryczne

Definicja 0.11: Drogowe

Oświetlają drogę na min 100m

Definicja 0.12: Przeciwmgłowe tylne

Włączamy gdy widoczność ≤ 50m

Definicja 0.13: Awaryjne i kierunkowskazy

Częstotliwość mrugania 90 cykli na minutę, ± 30

Wskazówka 4: Pytanie testowe

Przyczyna zwiększonej częstotliwości mrugania świateł awaryjnych
Odpowiedź: przepalona żarówka

Płyny

Olej

Przebieg sprawdzenia poziomu oleju

- Na równej nawierzchni
- Przy chłodnym silniku
- Wyciągnąć, przetrzeć, włożyć z powrotem
- Wyciągnąć jeszcze raz i sprawdzić: poziom powinien się znajdować między minimum a maksimum

Płyn chłodzący i hamulcowy

Wskazać min i max, stwierdzić że jest między min a max

Wskazówka 5: Dostosowanie lusterek

Widzieć w dolnym kącie klamkę tylnych drzwi (w lewym lustrze w prawym kącie i na odwrót)

Parkowanie

Kryteria:

- Równolegle do innych samochodów
- Zajmuje jedno stanowisko
- Można swobodnie otworzyć drwi i wyjść

Rodzaje:

- Skośne (wjazd przodem, wyjazd tyłem)
- Prostopadłe (przodem lub tyłem) — **najczęściej się trafia**
- Równoległe (wjazd tyłem, wyjazd przodem)

Wskazówka 6: Zmiana biegów

Zmieniamy biegi jeśli częstotliwość obrotów silnika jest około 2000 ob/min

Droga

Definicja 0.14: Jezdnia

Część drogi przeznaczona do ruchu pojazdów

Definicja 0.15: Pas ruchu

Część jezdni przeznaczona do ruchu pojazdów wyznaczona **lub niewyznaczona** przez znaki drogowe

Definicja 0.16: Strefa ruchu

Droga wewnętrzna na której obowiązują przepisy jak na drogach publicznych

Rysunek 7: D-52: Strefa ruchu

Wskazówka 7: Pobocze

Jeśli pobocze jest oddzielone linią przerywaną, możemy zatrzymać się na poboczu, jeśli nie, to nie

Autostrada

Rysunek 8: D-9: Autostrada

Może wjechać tylko pojazd samochodowy (bez czterokołowca), który może rozwijać prędkość od 40 km/h

Prędkość maksymalna: 140 km/h

Achtung! 1

Nie ma minimalnej prędkości
Nie wolno holować

Droga ekspresowa

Rysunek 9: D-7: Droga ekspresowa

Może wjechać tylko pojazd samochodowy (bez czterokołowca)

Mogą występować skrzyżowania i miejsca do zawrócenia

Prędkości maksymalne:

- 1 jezdniowa — 100 km/h
- 2 jezdniowa — 120 km/h

Tunel



Rysunek 10: D-37: Tunel

Jeśli jest poza obszarem zabudowanym oraz długość tunelu jest przynajmniej 500m, to musimy zachować odległość 50m. Jeśli jest zatrzymanie (wypadek etc) — minimum 5m

---

2026-02-18

Znaki ostrzegawcze

Znaki ostrzegawcze są instalowane na odległości od obiektu:

- Prędkość maksymalna do 60 km/h: do 100 m (A-7: do 25m)
- Prędkość maksymalna od 60 km/h: 150 – 300m (A-7: do 50m)

Achtung! 2: Niebezpieczne zakręty

Znaki Dwa niebezpieczne zakręty **kierunku drugiego zakrętu nie określają**:

Rysunek 11: A-3: Niebezpieczne zakręty – **pierwszy** w prawo

Rysunek 12: A-4: Niebezpieczne zakręty – **pierwszy** w lewo

Wyprzedzanie

Nie wolno wyprzedzać:

- po znaku zakaz wyprzedzania
- na przejściach dla pieszych i przejazdach dla rowerzystów (oprócz tych gdzie ruch jest kierowany)
- na niebezpiecznych zakrętach (oprócz drogi jednokierunkowej lub jeśli nie wjeżdżamy na przeciwny pas ruchu: po 2 pasy ruchu)
- przy dojeżdżaniu do wierzchołka wzniesienia (takie same wyjątki jak powyżej)
- na przejazdach kolejowych
- na skrzyżowaniach (oprócz jeśli ruch jest kierowany lub jest o ruchu okrężnym)

- jeśli najeżdżamy na linię ciągłą pojedynczą lub podwójną

Możemy wyprzedzić z prawej strony jeśli:

- pojazd przed nami zjechał do pasa po lewej by skręcić w lewo
- w obszarze zabudowanym: mamy ≥ 2 **wyznaczone** pasy
- poza: mamy ≥ 3 **wyznaczone** pasy (nie dotyczy jednokierunkowej, na niej od 2)

Achtung! 3

Na autostradach możemy wyprzedzić z prawej strony, bo jest to jezdnia jednokierunkowa z ≥ 2 pasami ruchu

Trójkąt awaryjny

Ustawiamy na odległości od pojazdu:

- Na obszarze zabudowanym — tuż za pojazdem lub na pojeździe na wysokości do 1 metra
- Poza obszarem zabudowanym — 30 metrów
- Na drodze szybkiego ruchu — 100 metrów

Przystanki

Nie można się zatrzymywać w obrębie:

- znaku poziomego (“zygzaków”)
- zatoki
- 15m od znaku jeśli nie ma linii i zatoki

Przejazdy kolejowe

Oznaczane są tak zwanymi Krzyżami świętego Andrzeja:

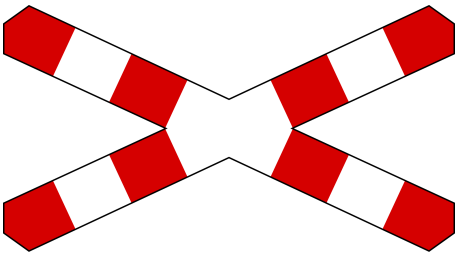

Rysunek 13: G-3: Jednotorowy przejazd kolejowy

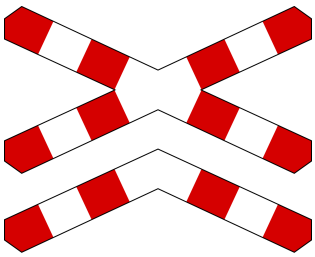

Rysunek 14: G-4: Wielotorowy przejazd kolejowy

Krzyż świętego Andrzeja instalowany jest w 5-8 metrach od pierwszej szyny. Jak nie widzimy linii zatrzymania, zatrzymujemy się przed krzyżem

Wskazówka 8

Wjeżdżamy na przejazd na małym biegu, nie zmieniamy biegów na przejeździe

Znaki poprzedzające

Rysunek 15: A-9: Przejazd kolejowy z zaporami

Rysunek 16: A-10: Przejazd kolejowy bez zapór

Dodatkowo są umieszczane G-1* według następujących reguł:

- Znak A-9 lub A-10 wraz ze znakiem z trzema paskami jest odległy tak samo jak inne znaki ostrzegawcze (patrz Znaki Ostrzegawcze)

- Z dwoma paskami jest odległy o $\frac{2}{3}$ odległości znaku z trzema paskami od przejazdu
- Z jednym paskiem — $\frac{1}{3}$ odległości (bliżej niego nie)

Rysunek 17: G-1a: Słupek z trzema paskami

Achtung! 4: Zatrzymanie obok przejazdu

- Nie wolno się zatrzymać w odległości 10 m od przejazdu
- Nie wolno postojować na odległości bliżej znaku z jednym paskiem

Zatrzymania i postoje

Definicja 0.17: Zatrzymanie

Unieruchomienie pojazdu do 1 min nie wynikające z warunków lub przepisów **lub** o dowolnej długości wynikające z przepisów lub warunków

Achtung! 5

Na mostach nie wolno się zatrzymać lub cofnąć

Definicja 0.18: Postój

Unieruchomienie pojazdu które nie jest zatrzymaniem

2026-02-20

Wskazówka 9: Wzniesienie

Zjeżdżamy ze stromego wzniesienia na tym samym biegu co na nie wjeżdżaliśmy

Holowanie

- Po lewej stronie z tyłu pojazdu holowanego ma być umieszczony trójkąt ostrzegawczy
- Prędkość:
  - na obszarze zabudowanym — 30 km/h
  - poza — 60 km/h
- Długość linki: 4-6 m

Achtung! 6

Nie włączamy kierunkowskazu jeśli po zatrzymaniu kontynuujemy jazdę w tym samym kierunku

Achtung! 7: Autobusy szkolne (gimbusy)

Włączając się do ruchu mają pierwszeństwo w każdym przypadku.
Jeśli dodatkowo z przodu i tyłu ma znak STOP, musimy zatrzymać się i czekać usunięcia znaku.

Wskazówka 10

Jeśli na całej jezdni możliwy jest tylko jeden kierunek ruchu, możemy skręcać tam z dowolnego pasa

Wskazówka 11

Na rondzie musimy włączyć kierunkowskaz na wysokości linii środkowej drogi poprzedzającej drogą na którą zjeżdżamy

Achtung! 8

Tramwaj zjeżdżający z ronda **zawsze** ma pierwszeństwo

Zawracanie

Rysunek 18: S-3: Tylko **skręcić** w lewo

Rysunek 19: S-3: Tylko **zawrócić**

Rysunek 20: S-3: **Skręcić** lub **zawrócić**

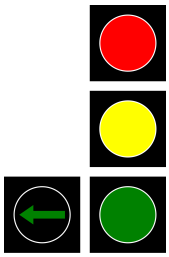

Rysunek 21: S-2: **Możemy** zawrócić

Achtung! 9

S-2: jeśli jest czerwony i świeci się strzałka musimy się zatrzymać przed linią bezwarunkowego zatrzymania

Nie możemy zawrócić przy znaku:

- Zakaz skrętu w lewo **tylko na najbliższym skrzyżowaniu**
- Zakaz zawracania **na całym odcinku do skrzyżowania i na skrzyżowaniu**
- Nakaz jazdy w lewo

Koniec zakazów



Rysunek 22: B-42: Koniec zakazów

Znak “Koniec zakazów” odwołuje znaki zakazu:

- zawracania
- wyprzedzania (oba)
- używania sygnału dźwiękowego
- ograniczenie prędkości